Universidad Peruana de Ciencias Aplicadas
Ingeniería de Software

Aplicaciones para dispositivos Móviles
2026-10

NRC: 3821
PROFESOR: Mayta Guillermo, Jorge Luis

Nombre del Producto: FirstCommit

Integrantes:

Apellidos, Nombres	Código
Velarde Gonzales, Néstor Hernán	U20211C221
Curi Marcelo, Angelo Marcio	U202022387
apellido, nombres	codigo
apellido, nombres	codigo
apellido, nombres	codigo

Lima, 16 de abril del 2026

Registro de Versiones del Informe

Versión	Fecha	Autor(es)	Descripción de la modificación
1.0	05/04/2026	Velarde Gonzales, Néstor Hernán	Creación inicial del documento

Project Report Collaboration Insights

Contenido

- **Capítulo I: Presentación**
  - 1.1. Startup Profile
    - 1.1.1. Descripción de la Startup
    - 1.1.2. Perfiles de integrantes del equipo
  - 1.2. Solution Profile
    - 1.2.1. Antecedentes y problemática
    - 1.2.2. Lean UX Process
      - 1.2.2.1. Lean UX Problem Statements
      - 1.2.2.2. Lean UX Assumptions
      - 1.2.2.3. Lean UX Hypothesis Statements
      - 1.2.2.4. Lean UX Canvas
  - 1.3. Segmentos objetivo
- **Capítulo II: Requirements Development and Software Solution Design**
  - 2.1. Competidores
    - 2.1.1. Análisis competitivo
    - 2.1.2. Estrategias y tácticas frente a competidores
  - 2.2. Entrevistas
    - 2.2.1. Diseño de entrevistas
    - 2.2.2. Registro de entrevistas
    - 2.2.3. Análisis de entrevistas
  - 2.3. Needfinding
    - 2.3.1. User Personas
    - 2.3.2. User Task Matrix
    - 2.3.3. User Journey Mapping
    - 2.3.4. Empathy Mapping
    - 2.3.5. Ubiquitous Language
  - 2.4. Requirements specification
    - 2.4.1. User Stories
    - 2.4.2. Impact Mapping
    - 2.4.3. Product Backlog
  - 2.5. Strategic-Level Domain-Driven Design
    - 2.5.1. EventStorming
      - 2.5.1.1. Candidate Context Discovery
      - 2.5.1.2. Domain Message Flows Modeling
      - 2.5.1.3. Bounded Context Canvases
    - 2.5.2. Context Mapping
    - 2.5.3. Software Architecture
      - 2.5.3.1. Software Architecture Context Level Diagrams
      - 2.5.3.2. Software Architecture Container Level Diagrams
      - 2.5.3.3. Software Architecture Deployment Diagrams
  - 2.6. Tactical-Level Domain-Driven Design

        - 2.6.x. Bounded Context:
            - 2.6.x.1. Domain Layer
            - 2.6.x.2. Interface Layer
            - 2.6.x.3. Application Layer
            - 2.6.x.4. Infrastructure Layer
            - 2.6.x.5. Bounded Context Software Architecture Component Level Diagrams
            - 2.6.x.6. Bounded Context Software Architecture Code Level Diagrams
                - 2.6.x.6.1. Bounded Context Domain Layer Class Diagrams
                - 2.6.x.6.2. Bounded Context Database Design Diagram

- **Capítulo III: Solution UI/UX Design**
    - 3.1. Product design
        - 3.1.1. Style Guidelines
            - 3.1.1.1. General Style Guidelines
        - 3.1.2. Information Architecture
            - 3.1.2.1. Organization Systems
            - 3.1.2.2. Labelling Systems
            - 3.1.2.3. SEO Tags and Meta Tags
            - 3.1.2.4. Searching Systems
            - 3.1.2.5. Navigation Systems
    - 3.1.3. Landing Page UI Design
        - 3.1.3.1. Landing Page Wireframe
        - 3.1.3.2. Landing Page Mock-up
    - 3.1.4. Mobile Applications UX/UI Design
        - 3.1.4.1. Mobile Applications Wireframes
        - 3.1.4.2. Mobile Applications Wireflow Diagrams
        - 3.1.4.3. Mobile Applications Mock-ups
        - 3.1.4.4. Mobile Applications User Flow Diagrams
        - 3.1.4.5. Mobile Applications Prototyping

- **Capítulo IV: Product Implementation & Validation**
    - 4.1. Software Configuration Management
        - 4.1.1. Software Development Environment Configuration
        - 4.1.2. Source Code Management
        - 4.1.3. Source Code Style Guide & Conventions
        - 4.1.4. Software Deployment Configuration
    - 4.2. Landing Page & Mobile Application Implementation
        - 4.2.1. Sprint n
            - 4.2.1.1. Sprint Planning n
            - 4.2.1.2. Sprint Backlog n
            - 4.2.1.3. Development Evidence for Sprint Review
            - 4.2.1.4. Testing Suite Evidence for Sprint Review
            - 4.2.1.5. Execution Evidence for Sprint Review
            - 4.2.1.6. Services Documentation Evidence for Sprint Review
            - 4.2.1.7. Software Deployment Evidence for Sprint Review
            - 4.2.1.8. Team Collaboration Insights during Sprint

- 4.3. Validation Interviews
  - 4.3.1. Diseño de Entrevistas
  - 4.3.2. Registro de Entrevistas
  - 4.3.3. Evaluaciones según heurísticas

- **Conclusiones**
  - Conclusiones y recomendaciones
  - Video App Validation
  - Video About the product
  - Video About the team

- **Glosario**

- **Bibliografía**

- **Anexos**

Student Outcome

ABET - EAC - Student Outcome 7

Criterio: La capacidad de adquirir y aplicar nuevos conocimientos según sea necesario, utilizando estrategias de aprendizaje apropiadas.

En el siguiente cuadro se describe las acciones realizadas y enunciados de conclusiones por parte del grupo, que permiten sustentar el haber alcanzado el logro del ABET – **EAC - Student Outcome 7**

Criterio específico	Acciones realizadas	Conclusiones
Actualiza conceptos y conocimientos necesarios para su desarrollo profesional y en especial para su proyecto en soluciones de software	-	-
Reconoce la necesidad del aprendizaje permanente para el desempeño profesional y el desarrollo de proyectos en soluciones de software.	-	-

Objetivos SMART

Capítulo I: Introducción

1.1. Startup Profile

1.1.1. Descripción de la Startup

Frock es una Startup que busca modernizar el transporte colectivo informal mediante **Chapaturuta**, una aplicación mobile que organiza y muestra la visibilidad de rutas, paraderos y horarios.

Nuestro objetivo es mejorar la conexión entre ciudades y distritos, facilitando información clara tanto para usuarios como conductores. Con esta solución aportamos orden sin perder la flexibilidad del servicio, ofreciendo una movilidad más accesible, eficiente y ajustada a las necesidades reales de las personas.

1.1.2. Perfiles de integrantes del equipo

Integrante	Perfil Profesional
Foto	Datos
Foto	Datos
Foto	Datos
Foto	Datos
Foto	Datos

1.2. Solution Profile

1.2.1. Nombre del producto

Nuestro producto **Chapaturuta** es una aplicación móvil desarrollada por el equipo de **Frock** que organiza y moderniza el transporte colectivo informal a través de información clara sobre rutas, paraderos y horarios que conecta ciudades y distritos brindando mayor accesibilidad y eficiencia para usuarios y conductores.

1.2.2. Antecedentes y problemática

En muchas regiones del Perú, especialmente en provincias y zonas rurales, los colectivos (autos compartidos que cubren rutas fijas entre pueblos o distritos) representan un medio de transporte esencial. Estas unidades operan de forma semiinformal, sin horarios estrictos ni plataformas digitales que informen sobre sus rutas, tarifas o paraderos. A pesar de su utilidad, la informalidad del servicio genera desinformación, falta de confianza y dificultad para planificar los viajes, especialmente para personas no familiarizadas con la zona. Es común que los pasajeros deban preguntar a transeúntes o esperar en puntos conocidos sin certeza del tiempo de espera o del costo del servicio.

Por otro lado, los conductores de colectivos enfrentan problemas para captar nuevos pasajeros, organizar eficientemente sus recorridos y diferenciarse en un mercado competitivo e informal. Esta situación genera ineficiencias tanto para usuarios como para operadores del servicio. En este contexto, surge la necesidad de una solución digital accesible que brinde visibilidad, organización y confianza al sistema informal de colectivos interurbanos, sin perder su flexibilidad, adaptándose a la realidad tecnológica y cultural de estas zonas.

La problemática se puede resumir en los siguientes puntos:

- **I. Desinformación sobre rutas y paraderos:** Los pasajeros no tienen acceso a información clara sobre las rutas disponibles, ubicación de los paraderos, horarios aproximados o tarifas. Esta falta de visibilidad dificulta la planificación del viaje y desalienta el uso del servicio, especialmente entre personas que no conocen la zona o viajan por primera vez.
- **II. Dependencia de canales informales:** En ausencia de señalización oficial o plataformas digitales, los usuarios deben confiar en el "boca a boca" o el conocimiento local para encontrar un colectivo. Esto limita el acceso al servicio y excluye a quienes no dominan estas redes informales, como turistas, personas mayores o nuevos residentes.
- **III. Falta de herramientas para conductores:** Los conductores operan sin apoyo tecnológico para anunciar su disponibilidad, comunicar sus rutas o gestionar sus viajes. Esto reduce su eficiencia, genera tiempos muertos y limita su capacidad para captar más pasajeros.
- **IV. Baja percepción de seguridad:** La falta de perfiles visibles y verificables de los conductores, así como la ausencia de información sobre los vehículos y las rutas, genera desconfianza. Esto impacta directamente en la decisión de uso del servicio, especialmente entre mujeres o personas en situación vulnerable.
- **V. Barreras tecnológicas en la adopción digital:** Muchos usuarios potenciales viven en zonas con conectividad limitada o tienen baja familiaridad con el uso de aplicaciones móviles. Las plataformas de transporte tradicionales no están diseñadas para este público, al requerir registros complejos, conexión permanente o interfaces poco intuitivas.
- **VI. Ausencia en el ecosistema de movilidad regional:** Al ser un sistema informal, los colectivos no están integrados en los planes de movilidad ni reciben soporte institucional. Esto contribuye a su invisibilidad como alternativa de transporte sostenible y eficiente en provincias del país.

1.2.3. Lean UX Process

1.2.3.1. Lean UX Problem Statement

Nuestra aplicación busca ayudar a personas que desean trasladarse de forma económica entre ciudades o pueblos cercanos, y que actualmente no cuentan con información clara ni accesible sobre dónde se ubican los paraderos de colectivos, sus rutas, horarios aproximados y tarifas.

Este problema afecta especialmente a viajeros locales, personas con recursos limitados o visitantes no familiarizados con la zona, que dependen del transporte colectivo para moverse de forma rápida y asequible. Al resolver este problema, esperamos que los usuarios puedan localizar fácilmente los puntos de embarque, planificar sus viajes con mayor confianza y acceder a una red de rutas informales que, aunque eficientes, hoy son invisibles para la mayoría.

1.2.3.2. Lean UX Assumptions

a. Business Outcomes Assumptions

- Creemos que al organizar y hacer visible el servicio de colectivos informales, podemos capturar un mercado desatendido en regiones con transporte público limitado.
- Creemos que ofrecer visibilidad a los conductores aumentará su volumen de pasajeros y generará tracción para monetizar la plataforma en el mediano plazo.
- Creemos que facilitar el acceso a transporte interurbano económico incrementará el uso de la aplicación y atraerá a aliados estratégicos (municipalidades, asociaciones de transporte, ONG,s de movilidad).

b. Users Assumptions

- Creemos que nuestros usuarios principales son personas entre 20 y 60 años, de nivel socioeconómico medio-bajo, que se movilizan entre distritos, pueblos o zonas periféricas.
- Creemos que actualmente encuentran colectivos preguntando en la calle, por recomendación o yendo a puntos conocidos, sin información clara o digital.
- Creemos que los conductores son independientes, operan de forma informal, y no usan ninguna app para captar pasajeros.

c. Users Assumptions

- Creemos que los pasajeros necesitan planificar sus viajes con confianza, saber dónde tomar el colectivo, cuánto pagar y en qué horario aproximado.
- Creemos que, si los conductores logran visibilizar su ruta, ubicación y disponibilidad, podrán captar más pasajeros de forma más eficiente.
- Creemos que los usuarios valorarán poder ubicar fácilmente colectivos, sin perder la flexibilidad del servicio.

d. Users Assumptions

- Creemos que una app móvil sencilla (desarrollada en **Flutter** para el segmento de pasajeros y en **Kotlin/Android** para el segmento de conductores), sin necesidad de registro obligatorio para el consultante, con geolocalización de paraderos y rutas, será suficiente para ayudar al pasajero.
- Creemos que perfiles de conductor con información básica (placa, tipo de vehículo, ruta habitual) mejorarán la percepción de seguridad.
- Creemos que el sistema debe adaptarse al funcionamiento flexible del colectivo (sin horarios fijos, rutas semi estables).

1.2.3.3. Lean UX Hypothesis

- **Hipótesis 1: Mapa con rutas y paraderos** Creemos que el objetivo de que más personas usen la aplicación para organizar sus viajes se logrará si los pasajeros interurbanos obtienen confianza y claridad sobre cómo tomar un colectivo con un mapa interactivo que muestre rutas disponibles, paraderos, horarios estimados y tarifas de referencia.

- **Hipótesis 2: Visibilidad de conductores** Creemos que aumentar la cantidad de pasajeros por viaje se logrará si los conductores de colectivos obtienen una mejor captación de pasajeros y reducción del tiempo de espera con una funcionalidad en la aplicación **Android (Kotlin)** que muestre su ruta, ubicación actual y hora estimada de salida a los usuarios cercanos que utilicen la aplicación **Flutter**.

- **Hipótesis 3: Perfil del conductor** Creemos que aumentar la confianza de los usuarios y su retención en la app se logrará si los pasajeros obtienen una mayor sensación de seguridad y legitimidad del servicio con un perfil de conductor que incluya información del vehículo, ruta habitual, calificaciones y verificación básica.

- **Hipótesis 4: Interfaz sin registro obligatorio** Creemos que aumentar la accesibilidad de la app y alcanzar a más usuarios en zonas con baja alfabetización digital se logrará si los pasajeros ocasionales obtienen acceso rápido y sin fricciones a la información de viaje con una interfaz sencilla que no requiera registro obligatorio.

1.2.3.4. Lean UX Canvas

1.3. Segmentos objetivo

1. Pasajeros

Este segmento está compuesto principalmente por personas que necesitan movilizarse entre zonas periféricas, pueblos cercanos o distritos colindantes donde el transporte público tradicional es limitado, ineficiente o inexistente.

Características demográficas:

- **Edad promedio:** 20 - 60 años.
- **Ocupación:** Trabajadores informales, comerciantes, estudiantes universitarios y técnicos, amas de casa.
- **Nivel socioeconómico:** Medio bajo a bajo.
- **Ubicación:** Viven en zonas urbanas periféricas o rurales con acceso limitado al transporte público.
- **Frecuencia de uso:** Diaria o inter diaria, especialmente en horarios punta.

Necesidades:

- Movilidad rápida, económica y flexible.
- Disponibilidad de transporte en horarios amplios (incluyendo temprano en la mañana y noche).
- Información clara sobre puntos de partida, paraderos, tarifas y horarios.

2. Conductores

Este grupo representa a los operadores informales que ofrecen servicios de transporte colectivo, mayoritariamente en vehículos particulares. Ellos cubren rutas establecidas entre distritos o pueblos, recogiendo y dejando pasajeros en puntos acordados o paraderos informales.

Características demográficas:

- **Edad promedio:** 30 - 55 años.
- **Ocupación:** Conductores independientes, en su mayoría informales.
- **Nivel educativo:** Secundaria completa en promedio.
- **Tipo de vehículo:** Autos sedán, minivanes, station wagon, en su mayoría propios.
- **Zona de operación:** Zonas periféricas, pueblos intermedios y distritos con alta demanda y poca oferta de transporte formal.

Motivaciones:

- Generar ingresos diarios de forma flexible.
- Maximizar recorridos eficientes con más pasajeros en menor tiempo.
- Contar con herramientas que les permitan ser más visibles y captar pasajeros fácilmente.

Capítulo II: Requirements & Analysis

2.1. Competidores

Criterio	Moovit	RedBus	QuickRide	Frock
Logo	Moovit	RedBus	QuickRide	The image you are requesting does not exist or is no longer available. imgur.com
Overview	Plataforma global para planificar viajes en transporte público, incluyendo colectivos y buses, con mapas, horarios y rutas.	Plataforma digital de compra de pasajes en buses interprovinciales en LATAM y Asia.	App india para compartir viajes al trabajo (carpooling) entre particulares con rutas fijas.	Plataforma enfocada en el transporte colectivo informal interurbano en zonas rurales y periféricas de Perú. Informa sobre paraderos, rutas, disponibilidad y tarifas.
Ventajas Competitivas	Amplia cobertura internacional, mapas en tiempo real, integración con transporte formal e informal.	Facilita pagos seguros y reservas anticipadas, alianzas con empresas de buses formales.	Permite compartir autos con rutas definidas entre compañeros de trabajo, bajo costo y menor congestión.	Adaptación cultural y tecnológica al entorno rural y periférico peruano, interfaz sin registro obligatorio, visibilidad de conductores informales, enfoque flexible e inclusivo.
Modelo de Negocio	Freemium para usuarios, venta de datos a operadores de transporte y gobiernos.	Comisión por pasaje vendido, acuerdos con empresas de transporte.	Comisión por viaje compartido, modelo B2C y B2B.	Modelo freemium: gratuito para usuarios, monetización a futuro por suscripciones o tarifas a conductores u organizaciones aliadas.

Criterio	Moovit	RedBus	QuickRide	Frock
Usuarios Objetivo	Usuarios urbanos y suburbanos que usan transporte público.	Usuarios que viajan entre ciudades con servicios de buses formales.	Profesionales que comparten auto en horarios laborales.	Pasajeros de zonas rurales o periurbanas (20-60 años), conductores informales independientes, municipios o asociaciones de transporte.
Tecnologías Clave	GPS, API de mapas, predicción de llegada, alertas de tráfico.	Pasarela de pago, integración con operadores formales.	Geolocalización, agrupación por rutas y horarios.	GPS, interfaz simple y perfiles verificados de conductor, mapeo colaborativo de rutas y paraderos.
Debilidades	Requiere conectividad constante, enfoque urbano.	No cubre colectivos ni rutas informales.	Limitado a carpooling urbano, no apto para zonas rurales.	Depende de la adopción digital en zonas con conectividad limitada; requiere mapeo inicial colaborativo.

2.2. Entrevistas

Para conocer a nuestros segmentos objetivos, se diseñaron preguntas en específico para conocerá a detalle sus experiencias diarias en el transporte sea viajes o como transportistas.

Preguntas Generales:

- ¿Cuál es su nombre?
- ¿Cuántos años tienes?
- ¿A qué se dedica actualmente?
- ¿En qué ciudad vive?

Preguntas para usuarios (Pasajeros):

- ¿Por qué eliges colectivo y no otra forma de transporte?
- ¿Has llegado a perder tiempo o equivocarte de lugar por no tener información?
- ¿Cómo sueles enterarte de qué colectivo tomar?
- ¿Alguna vez has tenido problemas para encontrar un paradero?
- ¿Te gustaría una aplicación móvil que te muestre los paraderos y rutas?
- ¿Qué tan confiable consideras la información que ves en redes o te dicen otros?
- ¿Te sentirías más tranquilo si pudieras ver una información concisa en un mapa antes de salir?
- ¿Sabes aproximadamente cuánto demora en salir un auto? ¿Te incomoda esperar?
- ¿Cómo sabes si todavía hay autos disponibles en ciertas horas?
- ¿Qué te gustaría ver en una App de colectivos? (rutas, horarios, mapas, precios, fotos...)

Líderes de ruta (Transportistas)

- ¿Cómo decides cuándo sale cada auto o bus?
- ¿Cuántos autos o buses de colectivo hay normalmente en la ruta?
- ¿Cómo se organizan los horarios y salidas?
- ¿En qué horarios hay más movimiento?
- ¿Los pasajeros te llaman? ¿Llegan directo al paradero?
- ¿Cómo se enteran los pasajeros de dónde están ustedes?
- ¿Alguna vez te han dicho que se perdieron o que no encontraron el paradero?
- ¿Te molestaría si alguien pone tu paradero en una App?
- ¿Tú mismo estarías dispuesto a dar información actualizada de horarios o rutas?
- ¿Preferirías que lo haga otra persona o tener una persona que te apoye?
- ¿Te interesaría aparecer como “empresa recomendada”?

Registro de entrevista a usuarios (Pasajeros)

A continuación, se demostrará las entrevistas realizadas a los usuarios (pasajeros) y los transportistas para conocer sus experiencias diarias en el transporte.

Entrevistador N 01:

- **Entrevistador:**
  - Nombre: Néstor Velarde Gonzales
- **Entrevistado:**
  - Nombre: Angel Mamani Cayampi
  - Edad: 20 años
  - Ocupación: Estudiante
  - Distrito: San Miguel
  - Link de video: Video

Imagen 01. Entrevista a Ángel

Se realizó una entrevista a Angel Mamani Cayampi, una Joven estudiante de 20 años que vive actualmente en distrito de San Miguel, Ángel actualmente se dedica a rubro de taxí desde hace unos años atrás, debido que es autofinancia sus estudios en un instituto para costear su carrera técnica, Mayormente los pasajeros no son satisfactorios como él lo espera, paraderos vacíos, pasajeros que cancelan el viaje a la ultima hora entre otros.

Conclusión de Entrevistas

2.3. Nedfinding

2.3.1. User Personas

User Persona - pasajeros Imagen:

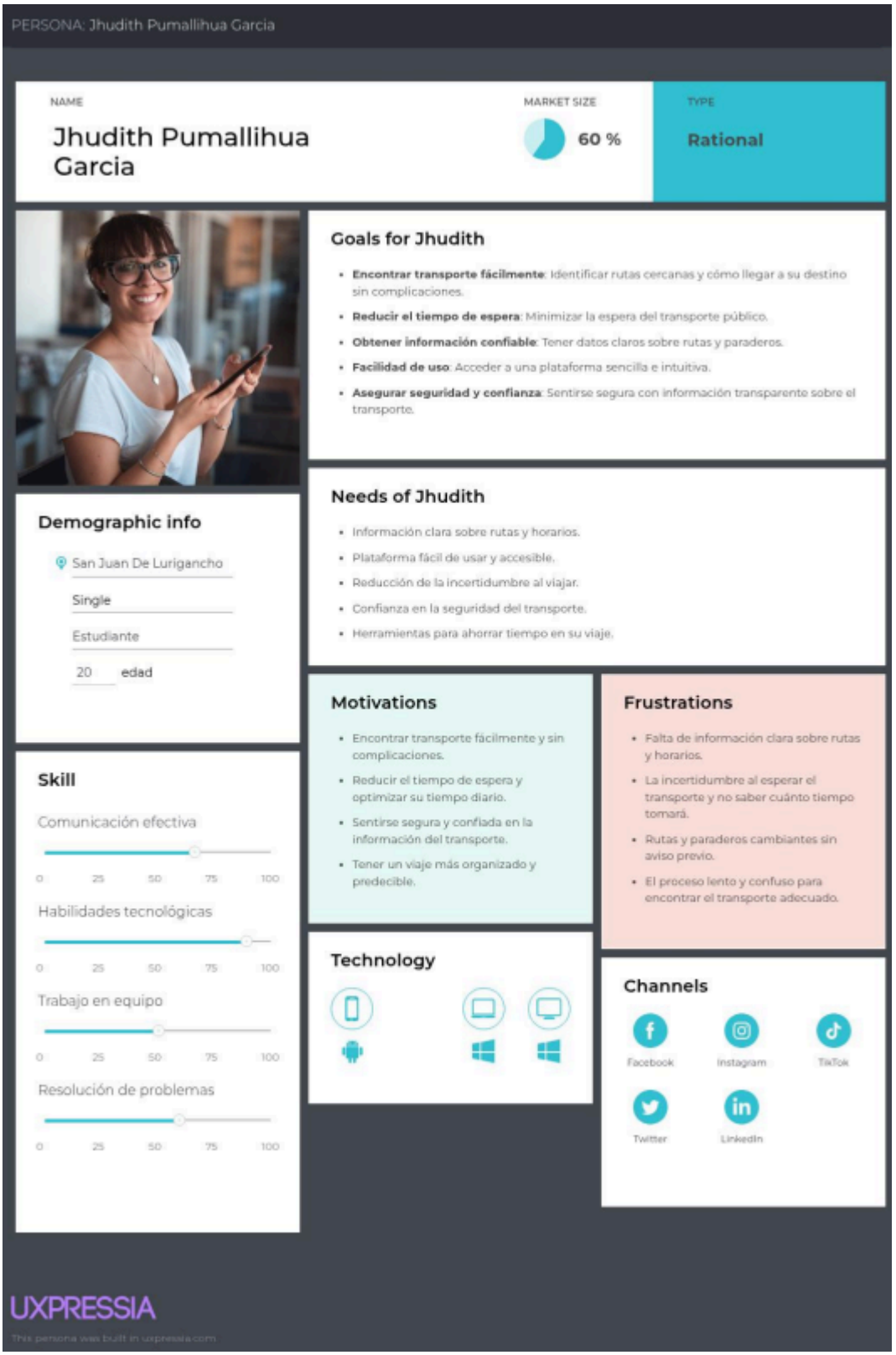

User Persona - conductores Imagen: Foto

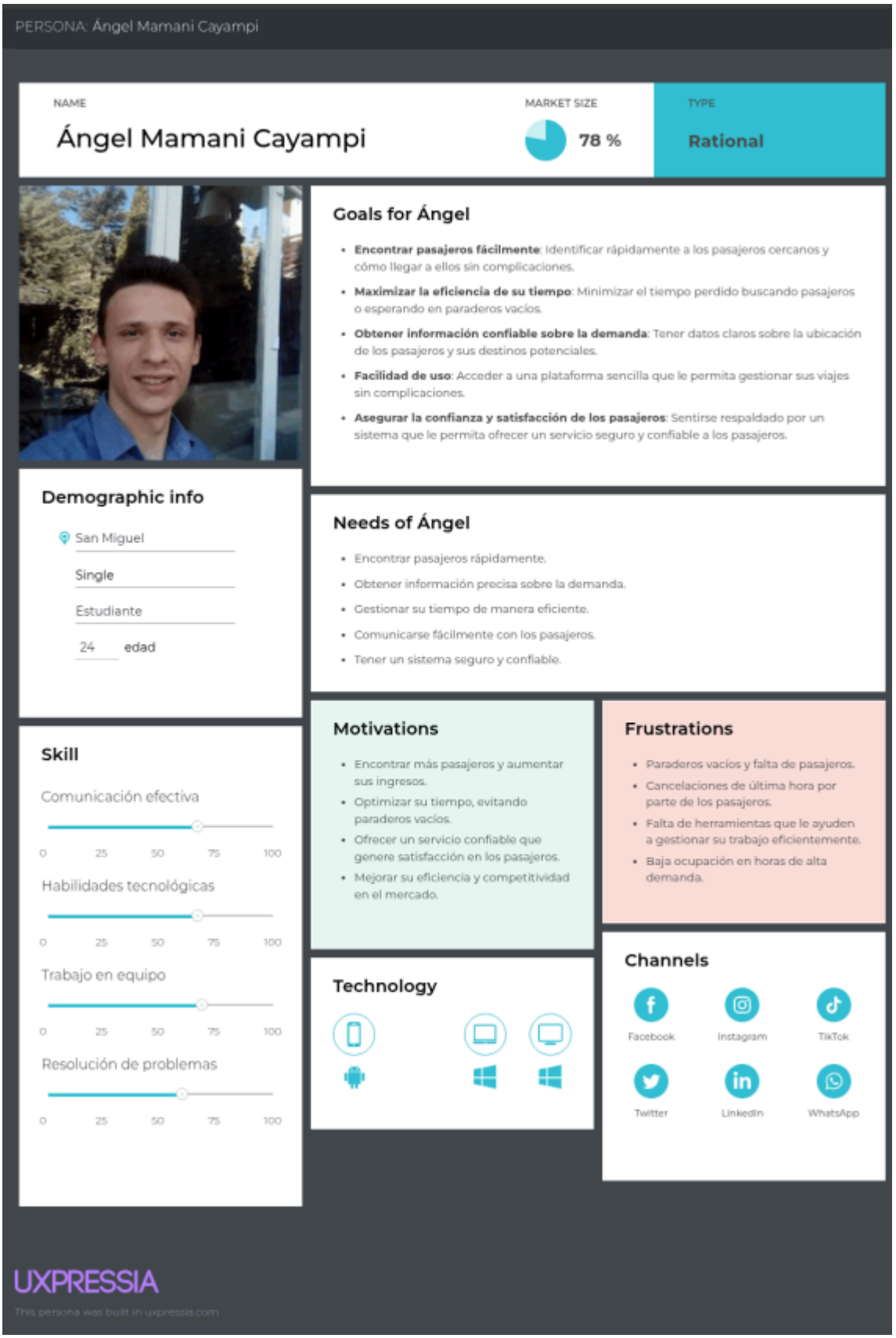

2.3.2. User Task Matrix

Los segmentos objetivo representados por los User Personas: Jesús Ramírez (pasajero interurbano) y Elmer Huamán (conductor de colectivo), serán una parte crucial para este 'User Task Matrix'. Las tareas listadas reflejan acciones que los usuarios ya realizan actualmente para alcanzar sus objetivos, independientemente del uso de una aplicación o tecnología. Esta matriz permite identificar oportunidades donde la solución digital de Frock puede generar mayor valor.

Task	User story ID	Carrier frequency	Carrier importance	Users frequency	Users importance
Buscar rutas disponibles para llegar a su destino	**US01**	High	High	Medium	High
Identificar paraderos adecuados para abordar	**US02**	High	High	Medium	Medium
Ver información del conductor	**US03**	Media	High	Medium	High
Avisar disponibilidad a pasajeros frecuentes	**US08**	Low	Medium	Alta	High
Ajustar su horario según los momentos de mayor demanda	**US09**	Low	Medium	Alta	High
Recordar o registrar los viajes que ha hecho	**US05**	Medium	Low	Low	Low
Evaluar la experiencia del viaje con un conductor	**US04**	Medium	High	Medium	Medium

2.3.3. Empathy Maps

Conductor:

PERSONA: Empathy map Chofer

1.WHO are we empathizing with?

Con **Ángel Mamani**, estudiante de 20 años, que trabaja como taxista/colectivero para financiar sus estudios en San Miguel.

Enfrenta dificultades para captar pasajeros, organiza sus salidas de manera empírica y sufre cancelaciones de último minuto, lo que genera pérdidas de tiempo y dinero.

7.What do they THINK and FEEL?

🤔Siente frustación cuando los pasajeros no aparecen o cancelan.
🤔Se preocupa porque los tiempos muertos afectan su ingreso económico
🤔Percibe que la falta de organización reduce su competividad.

2.What do they need to DO?

✔Captar suficientes pasajeros para que cada viaje sea rentable.
✔ Organizar mejor horarios y salidas de la ruta.
✔ Reducir la incertidumbre y los tiempos muertos en paraderos vacíos.
✔ Comunicar su disponibilidad y ubicación de forma clara a los usuarios.

6.What do they HEAR?

💡 Reclamaciones de pasajeros por demoras o falta de claridad de rutas.

💡 Comentarios de otros choferes sobre la baja demanda o problemas de ruta.

💡 Queja de pasajeros por no encontrar el paradero fácilmente.



3.What do they SEE?

👀 Paraderos vacíos, con poca afluencia de pasajeros

👀 Competencia de otros transportistas en la misma ruta.

👀 Pasajeros que muchas veces cancelan el viaje en el último momento.

5.What do they DO?

✔Sale a trabajar sin un horario definido, guiandose por la demanda del día
✔Espera en paraderos conocidos hasta captar pasajeros.
✔Recibe llamadas o mensajes informales de clientes conocidos.

PAINS

❌Cancelaciones de último momento que afectan sus ingresos

❌Paraderos vacíos y pérdida de tiempo de espera
❌Falta de canales efectivos para atraer pasajeros nuevos.

GAINS

✅ Mayor visibilidad de sus paraderos y horarios en una plataforma.
✅Mas pasajeros al reducir la incertidumbre y la informalidad
✅Organización eficiente de salidas y recorridos.

4.What do they SAY?

🗣 Los pasajeros no siempre llegan, a veces cancela el viaje a último minuto.
🗣Pierdo tiempo esperando en paraderos donde casi no hay gente.
🗣 Sería útil que los pasajeros supieran dónde estamos y cuándo salimos.

UXPRESSIA

This persona was built in uxpressia.com

Pasajero:

PERSONA: Empathy Mapping Pasajero

1.WHO are we empathizing with?

Con **Geraldine Sofia,** estudiante universitaria de 20 años en Chancay

Usa colectivos a diario para trasladarse porque son más rápidos y económicos, pero enfrenta problemas de **desinformación, inseguridad e incertidumbre** sobre las rutas y disponibilidad

7.What do they THINK and FEEL?

🤔Se siente frustada y estresada por perder tiempo en viajes mal planificadas
🤔Desconfía de la información que obtiene de terceros
🤔 Siente inseguridad al no conocer bien los paraderos o la disponibilidad de autos.

2.What do they need to DO?

✔Llegar a tiempo y sin complicaciones a sus destinos diarios.
✔Identificar de forma clara qué colectivo tomar y en qué paradero.
✔Reducir la incertidumbre en tiempos de espera y disponibilidad de autos.
✔ Contar con información confiable y práctica para planificar sus viajes.

6.What do they HEAR?

💡 Consejos de familiares, amigos sobre qué colectivo tomar

💡 Opiniones contradictorias de pasajeros sobre rutas y horarios.

💡 Comentarios negativos en redes sociales respecto a la informalidad.

3.What do they SEE?

👀 Paraderos poco visibles o cambiantes, sin señalización clara.

👀 Gente preguntando a otros qué colectivo tomar.

👀 Información dispersa en redes sociales o grupos de WhatSapp, muchas veces poco confiables.

5.What do they DO?

✔Pregunta a conocidos o transeúntes para saber qué colectivo tomar.
✔Se arriesga a esperar en paraderos sin certeza de tiempos.
✔Cambia de colectivo si se da cuenta que se equivocó de ruta.

PAINS

❌Desinformación sobre las rutas y paraderos.
❌Espera prolongada e incertidumbre en disponibilidad de autos
❌ Falta de confianza en redes o información informal.

GAINS

✅Información confiable y actualizada en un solo lugar
✅ Mapas con rutas, paraderos y precios visibles antes de salir.
✅ Menor tiempo de espera en paraderos, confianza y tranquilidad al salir.

4.What do they SAY?

🗣Muchas veces pierdo tiempo esperando o me equivoco de colectivo.
🗣La información de redes no siempre es confiable.
🗣 Me gustaría una app que muestre rutas, precios, horarios y paraderos en un mapa.

UXPRESSIA